[redacted]

Jing-Zhang AI Heritage Halo

[redacted]AI[redacted]

■■■■ / Design Concept

■■■■■■■■■■■■■■■■■——■■■■■■■■■■■■■■■■■■■■■■■■■■■■■■■■AI■■■■■■■■■■AI■■■■■■■■■■■■■■■■■■■■■■

■■	■■	■■■■■■■■	■■■■
G0	■■■ Readiness	■■/■■/■■/■■■■	halted
G1	■■■ Pilot	■■■■90■+■■■■	■■■
G2	■■■ Release	Go/No-Go■■■■■	■■■■
G3	■■■ Retirement	■■■■+■■■■	■■■

■■■■ / Site Overview

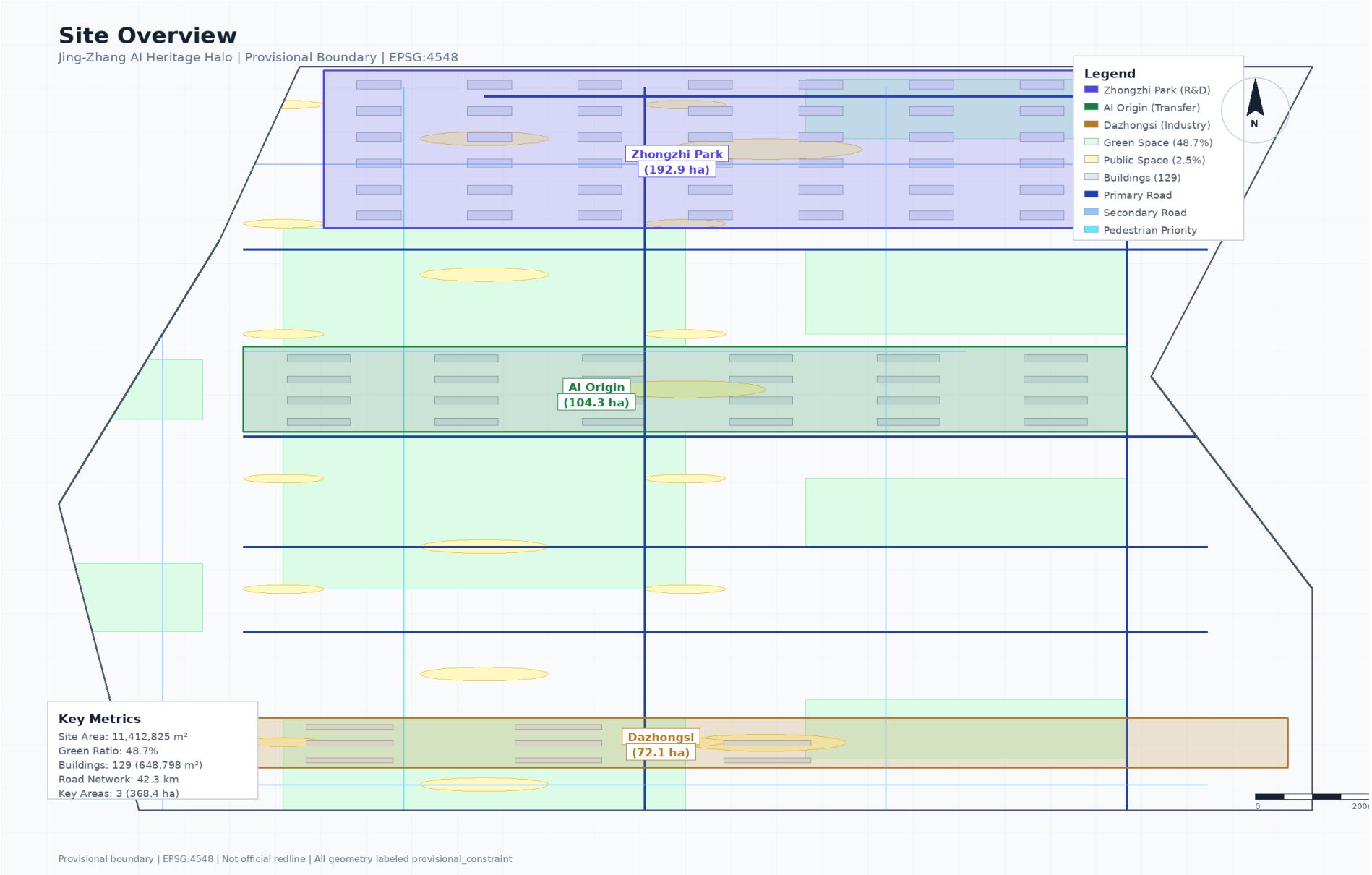

Provisional boundary | 11,412,825 m² | EPSG:4548

■■■■ / Land Use Structure

14■■■■7■■■■■■■100%■■■■■■■■■■■■■■■(■)→AI■■(■)→■■■(■)■■■■■■■■■■■■■■■



■■■■ / Key Areas

■■■■■■■■■■■■■■■■■■

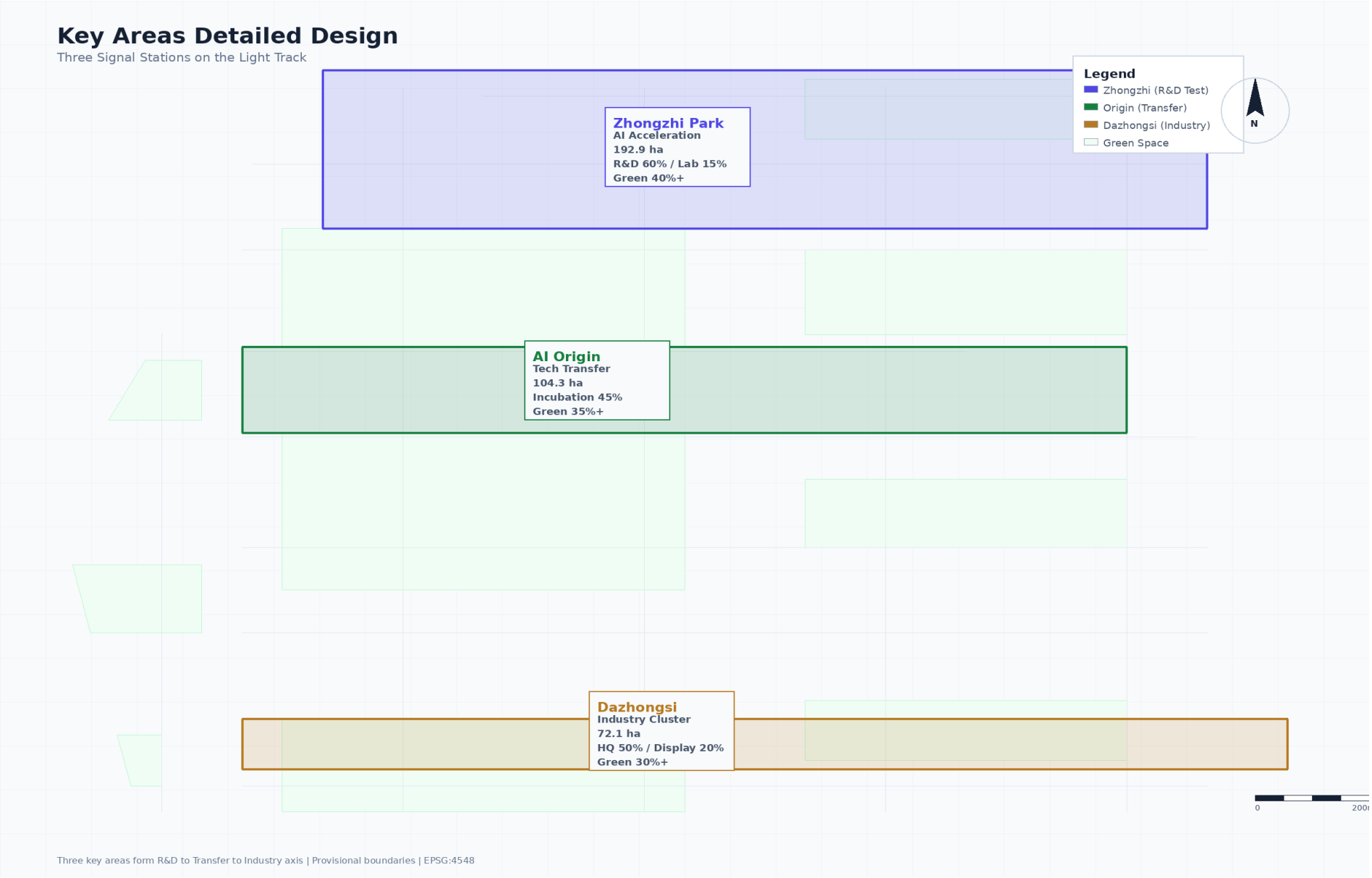
Key Areas Detailed Design
Three Signal Stations on the Light Track
Legend
Zhongzhi (R&D Test)
Origin (Transfer)
Dazhongsi (Industry)
Green Space
N
Zhongzhi Park
AI Acceleration
192.9 ha
R&D 60% / Lab 15%
Green 40%+
AI Origin
Tech Transfer
104.3 ha
Incubation 45%
Green 35%+
Dazhongsi
Industry Cluster
72.1 ha
HQ 50% / Display 20%
Green 30%+
0
Three key areas form R&D to Transfer to Industry axis | Provisional boundaries | EPSG:4548

[redacted]AI[redacted] (192.9 ha)

[redacted]2-3[redacted](60-80m)[redacted]4-6[redacted]AI[redacted]60%[redacted]15%[redacted]10%[redacted]15%[redacted]≥40%[redacted]

[redacted]	[redacted]	[redacted]	[redacted]
[redacted]	1.5km	[redacted]	[redacted]
[redacted]	12,000 m²	[redacted]	[redacted]
[redacted]	5,000 m²	[redacted]	[redacted]
[redacted]	8,000 m²	[redacted]	[redacted]

■■Al■■■■ (104.3 ha)

■■■■■■■■■■■■■■■■■■3-5■■■■■■■■■■6-8■■■■■■■■■45%■■■■■■25%■■■■■■15%■■■15%■■■■≥35%■

■■	■■	■■	■■
■■■■■■■■■■	3,000 m²	■■	■■■■
■■■■■■	800m	■■	■■■■
■■-■■■■■■	3■	■■	■■■■
■■■■■■	20,000 m²	■■	■■

■■■AI■■■■■ (72.1 ha)

■■■■■■■■■■■■■■■■■■200m TOD(80-100m)■■■6-8■■■■■■■■■50%■■■■■■20%■■■20%■■■■■10%■■■■≥30%■

■■	■■	■■	■■
■■■■TOD■■■	200m■■	■■	■■■■
■■■■■■■	4■■■	■■	■■■■
■■■■■■	2,000 m²	■■	■■■■
■■■■■■	5,000 m²	■■	■■■■

AI■■■ / Scenario Cards

10■■■■■■■■■■■■■■■■■■■■■■■■■■■halted■

ID	■■	AI■■	■■■■
01	■■■■■	■■■■■/PR■■	■■■■■■■
02	■■■■■■	■■■■/■■■■	■■■■■■■
03	■■■■■■	■■■■/■■■■	■■+■■■
04	AI■■■■	■■■■/■■■	■■■■■■■
05	■■■■	■■■■■/■■	■■■■■
06	■■■■■	■■■■/■■	■■■■■■
07	■■■■■	■■■■/■■	■■■■
08	■■■■■	■■■■/■■	■■■■■
09	■■■■■	■■■■/■■	■■■■
10	AI■■■	■■■■/■■	■■■■■

■■■■■■■■■ / Mobility & Blue-Green

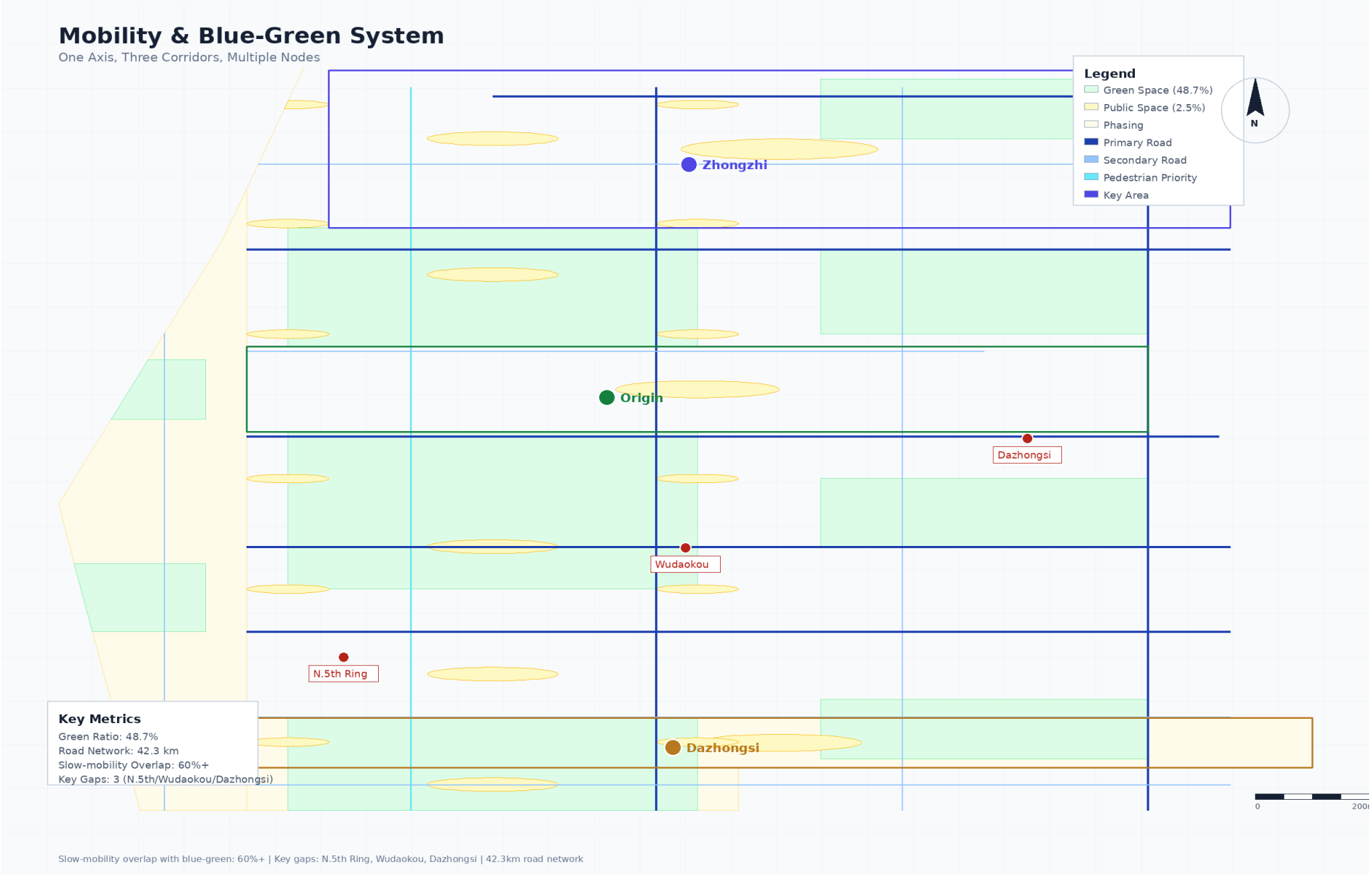

■■■■■■■■■■ / Projects & Four-Gate

ID	■■	■■	■■	■■
JZ-01	■■■■■■	■■■■/■■	■■(1-3■)	■■■
JZ-02	■■■■■■	■■/■■	■■(1-3■)	■■■
JZ-03	■■■■■	■■■■/■■	■■(3-7■)	■■■
JZ-04	■■■■■■■	■■/■■	■■(3-7■)	■■■
JZ-05	AI■■■■	■■■	■■■■(1-3■)	■■■
JZ-06	AI■■■■■	■■/■■	■■■■(1■■)	■■

■■■■■■■G0→G1→G2→G3■■■■■■■■■■90■■Go/No-Go■■■

■■■■ / Metrics

Metrics Evidence & Audit Chain

21 Spatial + 8 Concept-Specific Metrics | 4 Gates All PASS

Spatial Metrics (A-level)

Site Area:	11,412,825 m²
Green Ratio:	48.7%
Public Space:	2.5%
Building Footprint:	648,798 m²
Building Count:	129
Road Network:	42.3 km
Land Use Parcels:	14 (100% coverage)
Key Areas:	3 (368.4 ha)
Zhongzhi:	192.9 ha
AI Origin:	104.3 ha
Dazhongsi:	72.1 ha
Green Space Area:	5,561,347 m²
Public Space Area:	279,961 m²
FAR:	unknown (pending)
Building Height:	unknown (pending)
Constraints:	6 features
Phasing:	3 stages

Four-Gate Protocol

G0 Readiness
Ownership/Funding/Approval/Operator halted → awaiting G1

G1 Pilot
90-day lightweight trial + report not entered

G2 Release
Go/No-Go: acceptance + data + safety not reached

G3 Retirement
Public record + replacement + restore plan ready

Self-Check Status

Deterministic Validation: PASS
Spatial Review: PASS (3 provisional)
Visual Packaging: PASS
Professional Evidence: PASS

All 10 scenario cards HALTED | 0/10 field-verified | Structural completeness ≠ field pass

All metrics recalculable from GeoJSON | Four-gate protocol | 29 total metrics

■■■■ / User Journeys

J1: ■■■■■(■■■→■■■■→■■■→■■)
J2: ■■■■(■■→■■■■■→■■■■→■■■■■)
J3: ■■■■(■■■■→■■■■→■■■→■■■■→■■)
J4: ■■■■(■■■■→■■■■→■■■■→■■)

■■■■■■■■■■AI/■AI■■——■■G2■■■■■■■■■■0/4■■■■■■

■■■■■■ / Three-Zone Synergy

■■	■■■■	■■■■
AI■■■■■■	■■■+■■	■■■■■■■
■■■AI■■	■■■■+■■	■■■■■■■
AI+■■■■	■■■■+■■	■■■■■■■
■■■AI■■	■■■	■■■■+■■
AI■■■■■	■■■+■■■	■■■■■+■■■■■

■■■■■ / Risk & Compliance

■■■■■■provisional■8■■■■■■■■■AI■■■■■■■■■■■■■■■■■■■■■■■

■■	■■■	■■	■■
■■■■	■	■	■■■■/■■■■
■■■■	■	■	■■■■■■/■■■■■
■■■■	■	■	■■■■/■■■■
■■■■■■	■	■	■■■■/■■■■■■
■■■■	■	■	■■■/■■■■
■■■■	■	■	■■■■/■■■■

[redacted] / References

OFFICIAL-ANNOUNCEMENT: [redacted]
SITE-PACKAGE: [redacted]
BOUNDARY-SOURCE: [redacted]
SOURCE-REGISTRY: [redacted]
AGENT-TASKBOOK: [redacted]
PROCESSED-FACT-PACK: [redacted]
PROCESSED-MISSING-DATA-CHECKLIST: [redacted]
MOHURD-URBAN-DESIGN-MEASURES: [redacted]
MOHURD-CONTROL-DETAILED-PLANNING: [redacted]
MNR-LAND-USE-CLASSIFICATION-GUIDE: [redacted]